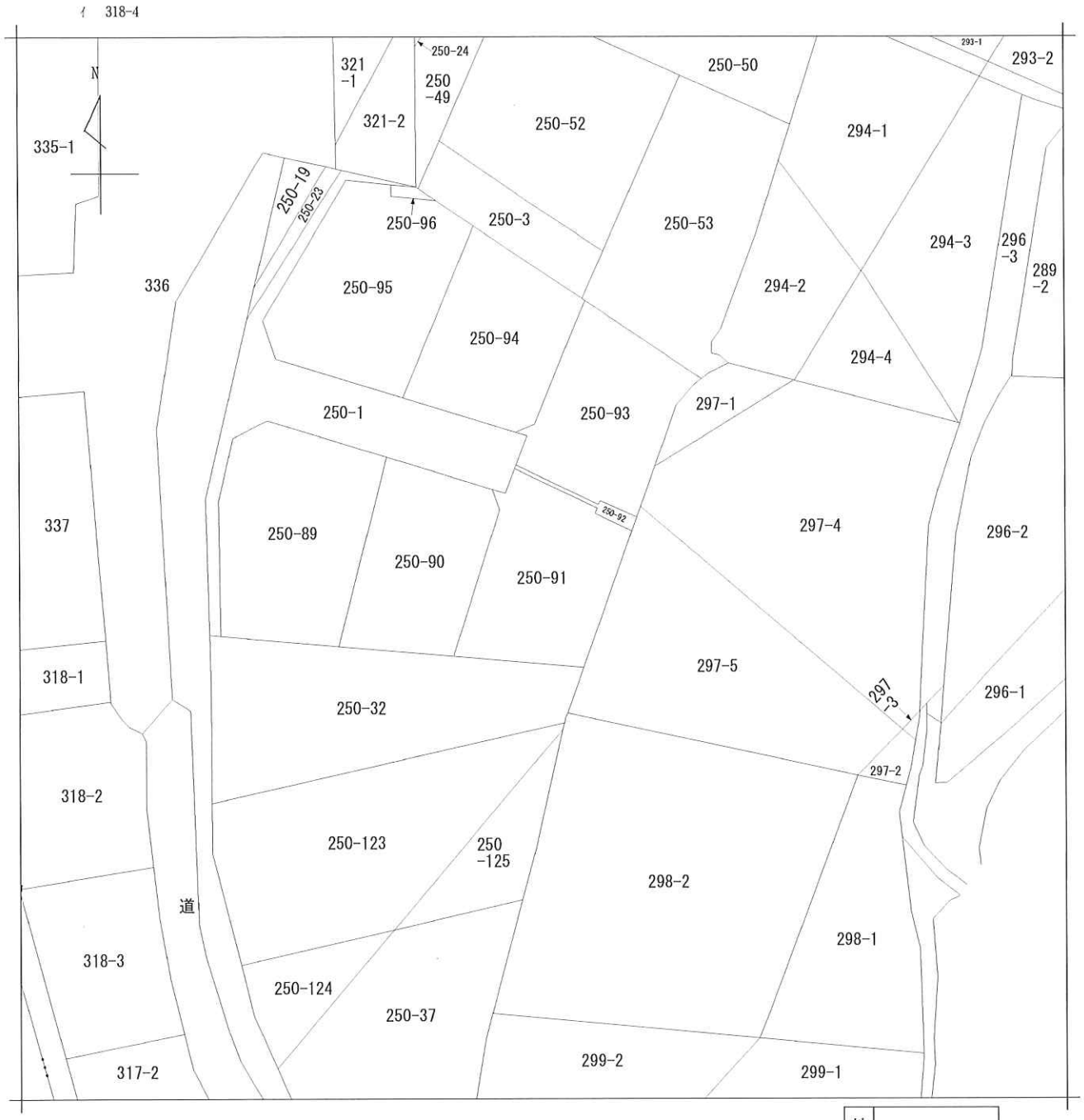
表示年月日：２０２５／０４／２１



地番区域見出	城山４丁目

請求部分	所在	小田原市城山四丁目			地番	250番91		
出力縮尺	1/300	精度区分		座標系番号又は記号		分類	地図に準ずる図面	種類	旧土地台帳附属地図
作成年月日				備付年月日(原図)		補記事項			

２０２５／１１／１４　１１：２８　現在の情報です。

表題部（主である建物の表示）	調製	平成１６年８月２６日	不動産番号	０２０３０００４００４４６
所在図番号	余白			
所在	小田原市城山四丁目　２５０番地９１		余白	
家屋番号	２５０番９１		余白	
①種類	②構造	③床面積　㎡	原因及びその日付〔登記の日付〕	
居宅	木造スレート葺２階建	１階　４７：５１ ２階　４２：９６	平成１５年９月８日新築 〔平成１５年９月１６日〕	
余白	余白	余白	昭和６３年法務省令第３７号附則第２条第２項の規定により移記 平成１６年８月２６日	

権利部（甲区）（所有権に関する事項）			
順位番号	登記の目的	受付年月日・受付番号	権利者その他の事項
１	所有権保存	平成１５年９月２４日 第２０１８４号	所有者　小田原市城山四丁目２０番１８号 土井　正好 順位１番の登記を移記
付記１号	１番登記名義人住所変更	令和７年７月１４日 第３２３０５号	原因　令和７年１月１７日住所移転 住所　兵庫県西宮市枝川町５番１５－１２０１号
	余白	余白	昭和６３年法務省令第３７号附則第２条第２項の規定により移記 平成１６年８月２６日
２	所有権移転	令和７年７月１４日 第３２３０７号	原因　令和７年７月１４日売買 所有者　平塚市見附町２９番１３号 株式会社シティクリエイション 会社法人等番号　０２１０－０１－０６２８７４

権利部（乙区）（所有権以外の権利に関する事項）			
順位番号	登記の目的	受付年月日・受付番号	権利者その他の事項
１	抵当権設定	平成１５年９月２４日 第２０１８５号	原因　平成１５年３月１１日保証委託契約による求償債権平成１５年９月２４日設定 債権額　金３，６００万円 損害金　年１４％（年３６５日日割計算） 債務者　小田原市城山四丁目２０番１８号 土井　正好 抵当権者　横浜市西区みなとみらい三丁目１番１号 横浜信用保証株式会社 共同担保　目録(さ)第１９５０号 順位１番の登記を移記
	余白	余白	昭和６３年法務省令第３７号附則第２条第２項の規定により移記 平成１６年８月２６日
２	１番抵当権抹消	令和７年７月１４日 第３２３０６号	原因　令和７年７月１４日主債務消滅
３	根抵当権設定	令和７年７月１４日 第３２３０８号	原因　令和７年７月１４日設定 極度額　金２，６００万円 債権の範囲　信用金庫取引　手形債権　小切手債権　電子記録債権 債務者　平塚市見附町２９番１３号 株式会社シティクリエイション 根抵当権者　平塚市紅谷町１１番１９号 平塚信用金庫 共同担保　目録(に)第６２２２号

共同担保目録				
記号及び番号	(さ)第１９５０号		調製	平成１７年５月２６日
番号	担保の目的である権利の表示	順位番号	予備	
１	小田原市城山四丁目　２５０番９１の土地	１	令和７年７月１４日受付第３２３０６号抹消	

2	小田原市城山四丁目　２５０番地９１　家屋番号　２５０番９１の建物	1	令和７年７月１４日受付第３２３０６号抹消
	余　白	余　白	平成１７年法務省令第１８号附則第１４条の規定により移記 平成１７年５月２６日
	余　白	余　白	令和７年７月１４日全部抹消

共　同　担　保　目　録			
記号及び番号	(に)第６２２２号	調製	令和７年７月１４日

番　号	担保の目的である権利の表示	順位番号	予　備
1	小田原市城山四丁目　２５０番９１の土地	3	余　白
2	小田原市城山四丁目　２５０番地９１　家屋番号　２５０番９１の建物	3	余　白

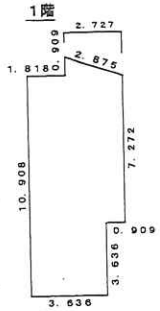
＊　「登記の目的」欄に「相続人申告」と記載されている登記は、所有権の登記名義人（所有者）の相続人からの申出に基づき、登記官が職権で、申出があった相続人の住所・氏名等を付記したものであり、権利関係を公示するものではない。
＊　下線のあるものは抹消事項であることを示す。

051671　各階平面図

建物図面
各階平面図

家屋番号	250番91
建物の所在	小田原市城山四丁目２５０番地９１

1階

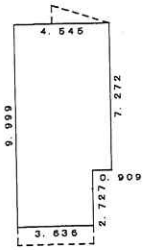


求積表

0. 909	×	2. 727 ／ 2	=	1. 2394
4. 545	×	7. 272	=	33. 0512
3. 636	×	3. 636	=	13. 2205
		計		47. 5111

床面積　47. 51 ㎡

2階

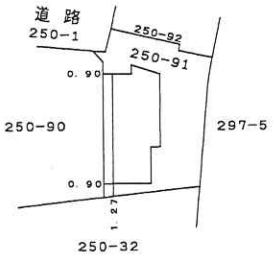


求積表

4. 545	×	7. 272	=	33. 0512
3. 636	×	2. 727	=	9. 9154
		計		42. 9666

床面積　42. 96 ㎡





作製者	小田原市栢新田42番地5 土地家屋調査士 渡部泰夫 平成15年 9月10日作製 登録第1208号	縮尺	1/250
申請人	土井正好	縮尺	1/500

15. 9. 16

（日本土地家屋調査士会連合会用紙）

（日調連12）

（日加納）

表示年月日：2025/04/21

２０２５／１１／１４　１１：２７　現在の情報です。

表　題　部　（土地の表示）		調製	平成１６年８月２６日	不動産番号	０２０３０００２６９５３１
地図番号	余　白	筆界特定	余　白		
所　在	小田原市城山四丁目			余　白	
①　地　番	②地　目	③　地　積　㎡		原因及びその日付〔登記の日付〕	
２５０番９１	宅地	１４７：０７		２５０番１から分筆 〔平成１４年１０月２１日〕	
余　白	余　白	余　白		昭和６３年法務省令第３７号附則第２条第２項の規定により移記 平成１６年８月２６日	

権　利　部　（甲区）　（所有権に関する事項）			
順位番号	登　記　の　目　的	受付年月日・受付番号	権　利　者　そ　の　他　の　事　項
１	所有権移転	平成１５年３月１１日 第４７７８号	原因　平成１５年３月１１日売買 所有者　小田原市東町一丁目２０番１８－４０７号コンセール小田原東町 土　井　正　好 順位２番の登記を移記
付記１号	１番登記名義人表示変更	平成１５年９月２５日 第２０３６１号	原因　平成１５年９月９日住所移転 住所　小田原市城山四丁目２０番１８号 順位２番付記１号の登記を移記
付記２号	１番登記名義人住所変更	令和７年７月１４日 第３２３０５号	原因　令和７年１月１７日住所移転 住所　兵庫県西宮市枝川町５番１５－１２０１号
	余　白	余　白	昭和６３年法務省令第３７号附則第２条第２項の規定により移記 平成１６年８月２６日
２	所有権移転	令和７年７月１４日 第３２３０７号	原因　令和７年７月１４日売買 所有者　平塚市見附町２９番１３号 株式会社シティクリエイション 会社法人等番号　０２１０－０１－０６２８７４

権　利　部　（乙区）　（所有権以外の権利に関する事項）			
順位番号	登　記　の　目　的	受付年月日・受付番号	権　利　者　そ　の　他　の　事　項
１	抵当権設定	平成１５年３月１１日 第４７７９号	原因　平成１５年３月１１日保証委託契約による求償債権同日設定 債権額　金３，６００万円 損害金　年１４％（年３６５日日割計算） 債務者　小田原市東町一丁目２０番１８－４０７号コンセール小田原東町 土　井　正　好 抵当権者　横浜市西区みなとみらい三丁目１番１号 横　浜　信　用　保　証　株　式　会　社 順位３番の登記を移記
付記１号	１番抵当権担保追加	余　白	共同担保　目録(さ)第１９５０号 平成１５年９月２４日付記 順位３番付記１号の登記を移記
	余　白	余　白	昭和６３年法務省令第３７号附則第２条第２項の規定により移記 平成１６年８月２６日
２	１番抵当権抹消	令和７年７月１４日 第３２３０６号	原因　令和７年７月１４日主債務消滅
３	根抵当権設定	令和７年７月１４日 第３２３０８号	原因　令和７年７月１４日設定 極度額　金２，６００万円 債権の範囲　信用金庫取引　手形債権　小切手債権　電子記録債権 債務者　平塚市見附町２９番１３号 株式会社シティクリエイション 根抵当権者　平塚市紅谷町１１番１９号 平　塚　信　用　金　庫 共同担保　目録(に)第６２２２号

共　同　担　保　目　録

記号及び番号	(さ)第１９５０号		調製	平成１７年５月２６日
番　号	担保の目的である権利の表示	順位番号	予　　備	
1	小田原市城山四丁目　２５０番９１の土地	1	令和７年７月１４日受付第３２３０６号抹消	
2	小田原市城山四丁目　２５０番地９１　家屋番号　２５０番９１の建物	1	令和７年７月１４日受付第３２３０６号抹消	
	余　白	余　白	平成１７年法務省令第１８号附則第１４条の規定により移記 平成１７年５月２６日	
	余　白	余　白	令和７年７月１４日全部抹消	

共　同　担　保　目　録

記号及び番号	(に)第６２２２号		調製	令和７年７月１４日
番　号	担保の目的である権利の表示	順位番号	予　　備	
1	小田原市城山四丁目　２５０番９１の土地	3	余　白	
2	小田原市城山四丁目　２５０番地９１　家屋番号　２５０番９１の建物	3	余　白	

＊　「登記の目的」欄に「相続人申告」と記載されている登記は、所有権の登記名義人（所有者）の相続人からの申出に基づき、登記官が職権で、申出があった相続人の住所・氏名等を付記したものであり、権利関係を公示するものではない。
＊　下線のあるものは抹消事項であることを示す。

054556

前 250－1　後・新同一・新

250-1 地積測量図 (1/2)

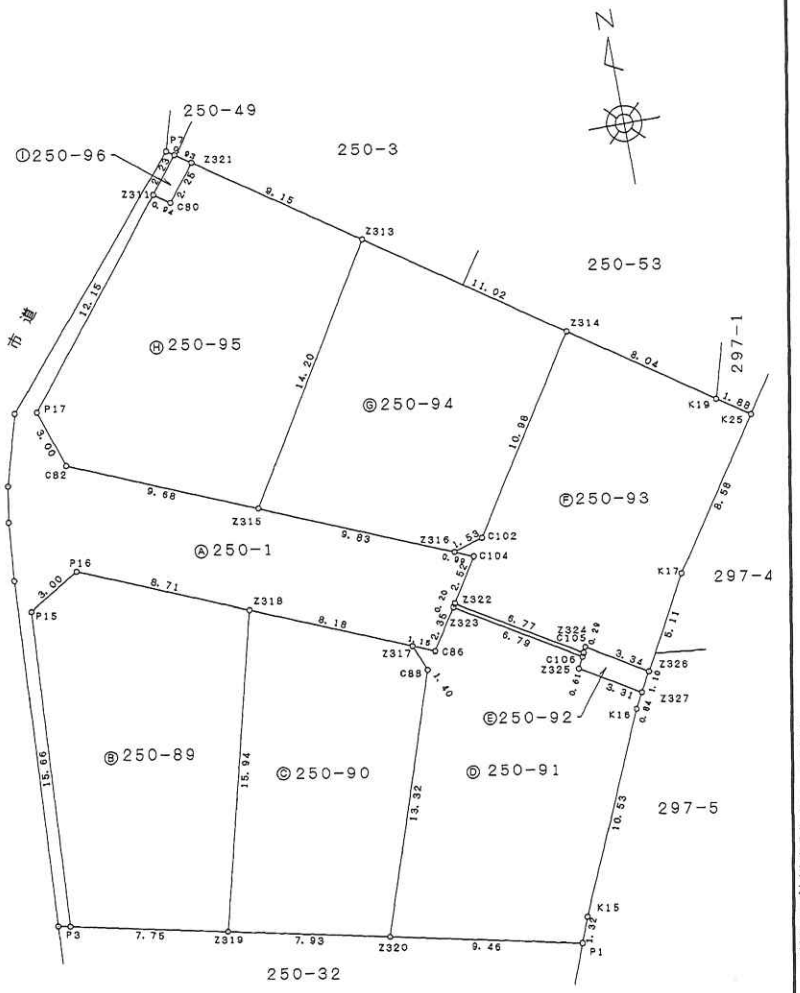
地番	250-89 ～250-96
土地の所在	小田原市城山４丁目

求積表

地番	Ⓑ 250-89				
NO	境界標	Xn	Yn	Yn+1－Yn-1	Xn・(Yn+1－Yn-1)
Z319	金属鋲	71.115	107.894	11.510	818.5336
Z318	プレート	86.563	111.827	-4.077	-352.9173
P16	プレート	89.985	103.817	-10.562	-950.4215
P15	プレート	88.408	101.265	-3.500	-309.4280
P3	プレート	72.770	100.317	6.629	482.3923
				合計	-311.8409
				合計面積	155.92045
				地積	155.92 ㎡

地番	Ⓒ 250-90				
NO	境界標	Xn	Yn	Yn+1－Yn-1	Xn・(Yn+1－Yn-1)
Z320	金属鋲	69.421	115.648	11.990	832.3577
C88	プレート	82.050	119.884	3.708	304.2414
Z317	プレート	83.346	119.356	-8.057	-671.5187
Z318	プレート	86.563	111.827	-11.462	-992.1851
Z319	プレート	71.115	107.894	3.821	271.7304
				合計	-255.3743
				合計面積	127.68715
				地積	127.68 ㎡

地番	Ⓓ 250-91				
NO	境界標	Xn	Yn	Yn+1－Yn-1	Xn・(Yn+1－Yn-1)
P1	コンクリート杭	67.402	124.890	9.714	654.7430
K15	金属鋲	68.640	125.362	4.714	323.5689
K16	金属鋲	78.284	129.604	4.645	363.6291
Z327	プレート	79.024	130.007	-2.420	-191.2380
Z325	プレート	80.766	127.184	-2.541	-205.2264
C106	プレート	81.312	127.466	-5.502	-447.3786
Z323	プレート	84.878	121.682	-7.049	-598.3050
C86	プレート	82.893	120.417	-2.326	-192.8091
Z317	プレート	83.346	119.356	-0.533	-44.4234
C88	プレート	82.050	119.884	-3.708	-304.2414
Z320	金属鋲	69.421	115.648	5.006	347.5215
				合計	-294.1594
				合計面積	147.07970
				地積	147.07 ㎡



作製者	足柄上郡開成町吉田島3地3 土地家屋調査士　石川徹　(平成14年10月7日作製)

(神奈川県土地家屋調査士会)

申請人	松浦建設株式会社 代表取締役　松浦秀和

縮尺 1/250

平成壱四年 10月 弐壱日 登記

14.10.21

登記年月日：平成14年10月21日

表示登記：2025/04/21

前 250－1 後・新同一・~~新~~

054557

地積測量図 (2/2)

地番	250－89 ～250－96 ← 250－1
土地の所在	小田原市城山４丁目

地番	Ⓔ 250－92				
NO	境界標	Xn	Yn	Yn+1－Yn－1	Xn・(Yn+1－Yn－1)
Z327	プレート	79.024	130.007	3.351	264.8094
Z326	プレート	79.994	130.535	-2.316	-185.2661
Z324	プレート	81.748	127.691	-2.977	-243.3637
C105	プレート	81.490	127.558	-5.902	-480.9539
Z322	プレート	85.046	121.789	-5.876	-499.7302
Z323	プレート	84.878	121.682	5.677	481.8524
C106	プレート	81.312	127.466	5.502	447.3786
Z325	プレート	80.766	127.184	2.541	205.2264
				合計	-10.0471
				合計面積	5.02355
				地積	5.02 ㎡

地番	Ⓕ 250－93				
NO	境界標	Xn	Yn	Yn+1－Yn－1	Xn・(Yn+1－Yn－1)
Z326	プレート	79.994	130.535	5.288	423.0082
K17	金属鋲	84.486	132.979	7.245	612.1010
K25	石杭	91.605	137.780	3.244	297.1666
K19	石杭	92.556	136.223	-8.158	-755.8876
Z314	プレート	97.253	129.622	-12.526	-1218.1910
C102	プレート	88.002	123.697	-7.392	-650.5107
Z316	プレート	87.559	122.230	-0.555	-48.5952
C104	プレート	87.170	123.142	-0.441	-38.4419
Z322	プレート	85.046	121.789	4.416	375.5631
C105	プレート	81.490	127.558	5.902	480.9539
Z324	プレート	81.748	127.691	2.977	243.3637
				合計	-279.4699
				合計面積	139.73495
				地積	139.73 ㎡

地番	Ⓖ 250－94				
NO	境界標	Xn	Yn	Yn+1－Yn－1	Xn・(Yn+1－Yn－1)
C102	プレート	88.002	123.697	7.392	650.5107
Z314	プレート	97.253	129.622	-3.118	-303.2348
Z313	プレート	103.550	120.579	-16.438	-1702.1549
Z315	プレート	91.419	113.184	1.651	150.9327
Z316	プレート	87.559	122.230	10.513	920.5077
				合計	-283.4386
				合計面積	141.71930
				地積	141.71 ㎡

地番	Ⓗ 250－95				
NO	境界標	Xn	Yn	Yn+1－Yn－1	Xn・(Yn+1－Yn－1)
Z315	プレート	91.419	113.184	16.301	1490.2211
Z313	プレート	103.550	120.579	-0.120	-12.4260
Z321	コンクリート杭	108.783	113.064	-8.911	-969.3653
C80	プレート	107.016	111.668	-2.158	-230.9405
Z311	金属鋲	107.570	110.906	-8.334	-896.4883
P17	プレート	98.068	103.334	-6.628	-649.9947
C82	プレート	95.219	104.278	9.850	937.9071
				合計	-331.0866
				合計面積	165.54330
				地積	165.54 ㎡

地番	① 250－96				
NO	境界標	Xn	Yn	Yn+1－Yn－1	Xn・(Yn+1－Yn－1)
C80	プレート	107.016	111.668	2.158	230.9405
Z321	コンクリート杭	108.783	113.064	0.630	68.5332
P7	プレート	109.316	112.298	-2.158	-235.9039
Z311	金属鋲	107.570	110.906	-0.630	-67.7691
				合計	-4.1993
				合計面積	2.09965
				地積	2.09 ㎡

総合計面積	884.80805 ㎡

地番	Ⓐ 250－1	
公簿	合計面積	残地
967.86	884.80805	83.05195
	地積	83.05 ㎡

地番	面積
Ⓐ 250－1	83.05195 ㎡
Ⓑ 250－89	155.92045 ㎡
Ⓒ 250－90	127.68715 ㎡
Ⓓ 250－91	147.07970 ㎡
Ⓔ 250－92	5.02355 ㎡
Ⓕ 250－93	139.73495 ㎡
Ⓖ 250－94	141.71930 ㎡
Ⓗ 250－95	165.54330 ㎡
Ⓘ 250－96	2.09965 ㎡

作製者	足柄上郡開成町吉田島 地3 土地家屋調査士 石川徹 (平成14年10月7日作製)
	(神奈川県土地家屋調査士会)

申請人	松浦建設株式会社 代表取締役 松浦秀和

縮尺 1／

14. 10. 21

平成壱四年 弐月壱日 登記